תשריט איחוד וחלוקת מגרשים בהסכמת הבעלים

מחוז :	מרכז
נפה :	רחובות
מקום :	**חפץ חיים**
גוש :	5449
חלקי חלקות :	6
גוש :	4729
חלקי חלקות :	3
מגרשים :	601 ,600
עפ"י תב"ע :	בר/4/282
שטח התכנית :	55.465 ד'
הוכן עבור :	קיבוץ חפץ חיים
קנה מידה :	1 : 1000

הועדה המקומית לתכנון ולבניה "שורקות"

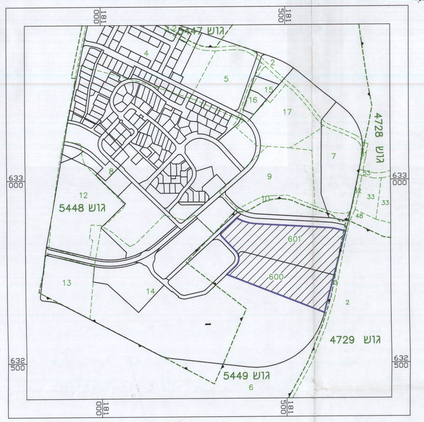
טבלת שטחים

מצב קיים			מצב מוצע		
יעוד	מס' מגרש	השטחים בדונמים	יעוד	מס' מגרש	השטחים בדונמים
תעשיה	600	23.960	תעשיה	600A	31.251
תעשיה	601	31.505	תעשיה	601A	24.214
סה"כ		55.465	סה"כ		55.465

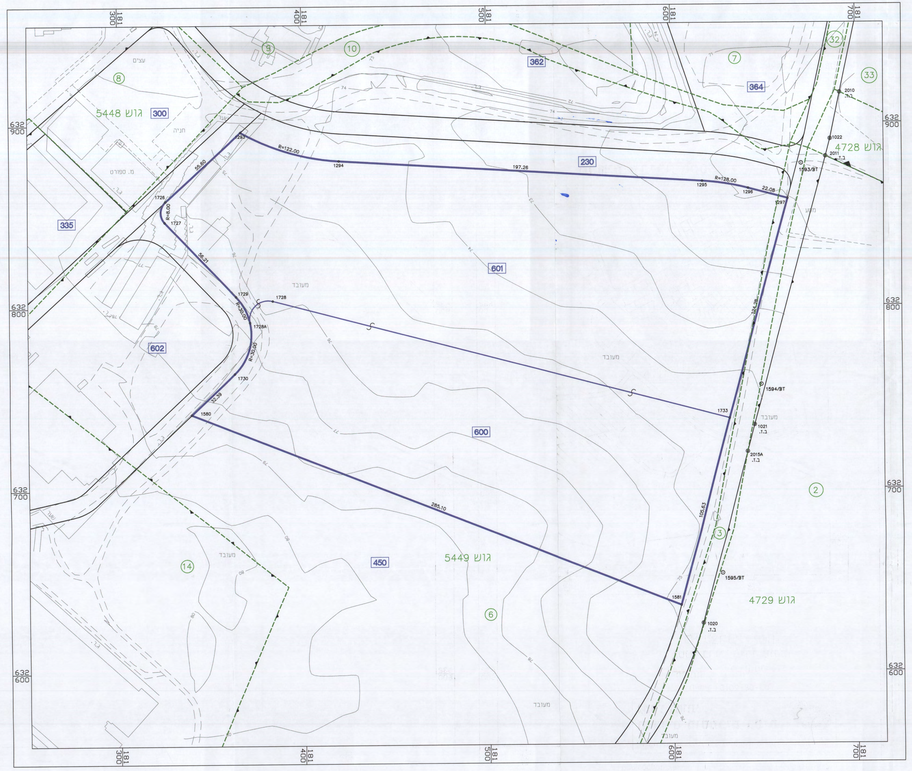
מקרא :

- גבול תוכנית
- גבול גוש רשום
- גבול חלקה רשומה
- מפלס מוצבי
- גבול מגרש / יעוד
- מס' חלקה רשומה ⑥
- מס' וא שטח מגרש, מוצע 600

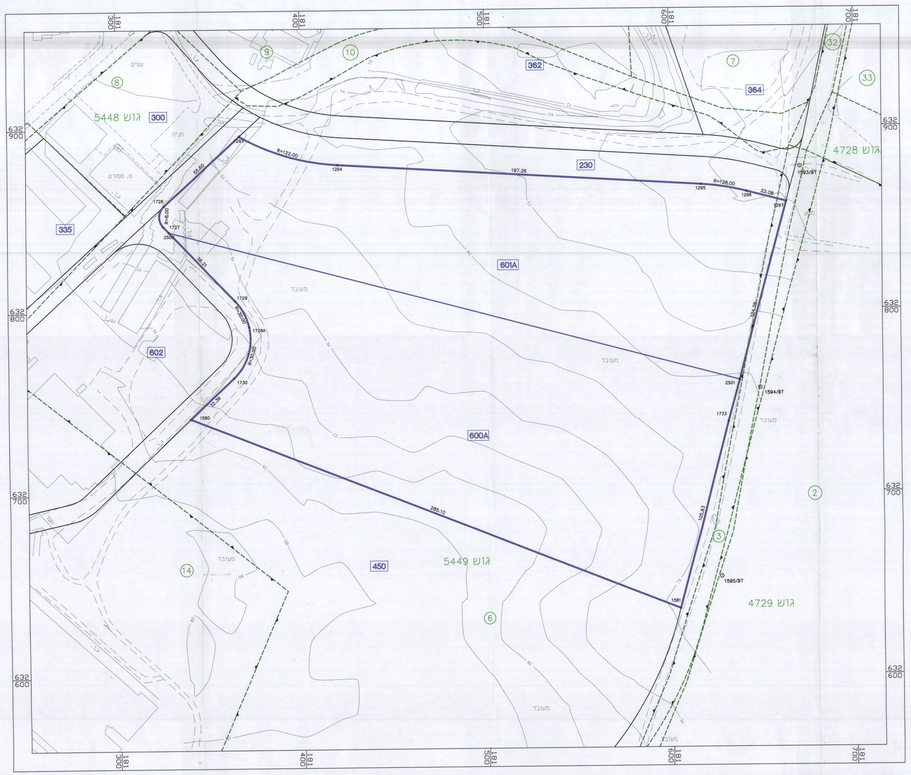
תרשים סביבה 1 : 5000



מצב מאושר קנ"מ 1 : 1000



מצב מוצע קנ"מ 1 : 1000



לא לצרכי רישום
גמניו ברני מודד מוסמך
רשיון מס 570
תאריך : 03-08-2010

גמניו ושות', מודדים מוסמכים בע"מ
רח' הרקפן 67, בני-ברק 51206 03-7541000,30 03-7516356,070

P:\2010\100506\e-register\tasrit haluka\index_100506.dwg

קיבוץ חפץ חיים
ועדת קבלה וועדים
למחיקת מיתקנים בע"מ

ועדת איזורית
נחל שורק

גני יל החרושת
מרחב עבודים למחיקת
הקצאת שימושים בעים

הערות:

1. גבולות החלוקות החדשה מתבצעי מחכנית בר/ 4/282 ובר/ 08/521/7
2. גבולות המגרשים המקובל עפי הסכם בין חפץ חיים לבר/ 282

1 9 AUG 2010

מס סידורי : ג.ב. / 10492

גרסה : 1

תאריך : 03-08-2010